Medio Ambiente
Secretaría de Medio Ambiente y Recursos Naturales

CONAGUA
COMISIÓN NACIONAL DEL AGUA

Información estadística para la Planeación Hídrica

Contenido

Presentación

A. Datos técnicos

a.1 Contexto general

a.2 Datos relevantes

Presentación

En el documento se presentan los datos técnicos que sirven de apoyo para dar contexto, analizar la situación y la problemática del sector hídrico en México.

Los datos técnicos se acompañan de una breve descripción de los mismos, que trata de ilustrar la situación actual del agua en México con el fin de dimensionar el impacto de las acciones a implementar en materia de Planeación Hídrica.

Este documento ha sido elaborado con el fin de integrar información básica para la planeación hídrica, debido a la pausa de mantenimiento del Sistema Nacional de Información sobre Cantidad, Calidad, Usos y Conservación del Agua (SINA), que entre otros propósitos que tiene, es servir de fuente de información para contribuir la planeación nacional.

A. Datos técnicos

a.1 Contexto general

Ciclo hidrológico

México recibe 1 464 734 hm^3 de agua a través de la precipitación:

- 71 % se evapotranspira y regresa a la atmósfera
- 22 % escurre por ríos y arroyos y
- 7 % se infiltra al subsuelo de forma natural, recargando los acuíferos.

Una parte del agua entra y otra sale del país a través de cuencas compartidas: al norte, con EUA y al sur, con Guatemala y Belice.

Agua renovable

El volumen de agua renovable[1] es de 471 713 hm^3.

Volúmenes medios anuales de los componentes del ciclo hidrológico en México, 2024

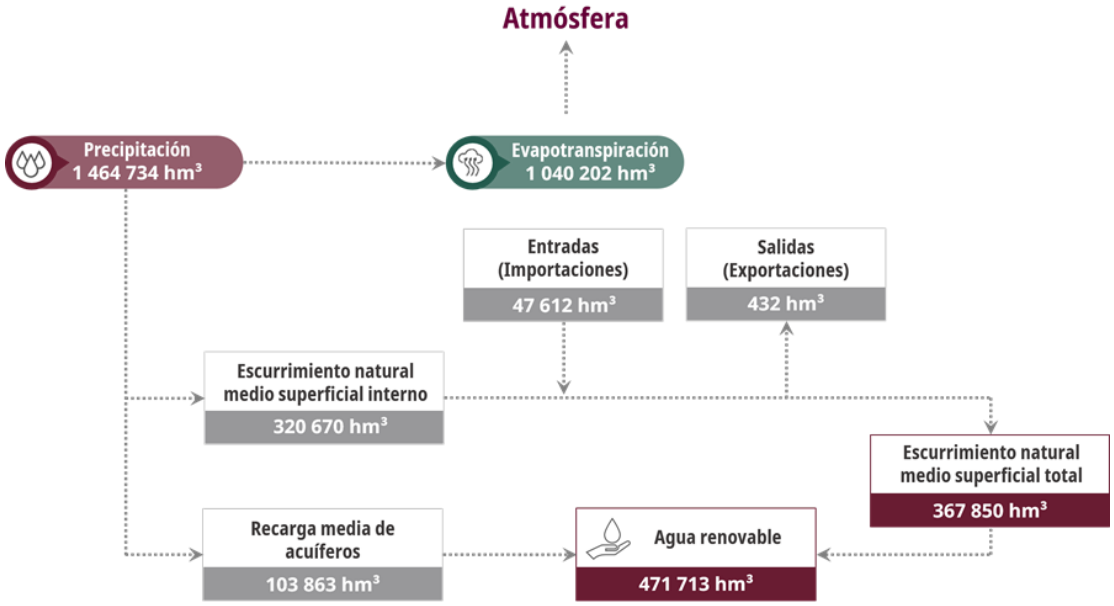

Fuente: CONAGUA. Subdirección General Técnica.

[1] Agua renovable: cantidad máxima de agua que puede ser extraída o utilizada anualmente en un área sin alterar el equilibrio ecológico, y que se repone a través del ciclo hidrológico, principalmente por la lluvia.

Precipitación

La precipitación promedio del país es 747.6 mm (periodo 1991-2020).

Su distribución espacial es irregular:

- En la zona sur-sureste supera los 2 300 mm/año
- En las zonas centro-norte y noroeste es menor a 400 mm/año.
- Los valores extremos se presentan en la Península de Baja California (159 mm/año) y en los estados de Chiapas y Tabasco (1 820 mm/año).

Así, dos terceras partes del territorio nacional son áridas o semiáridas.

Distribución espacial de la precipitación pluvial normal 1991-2020

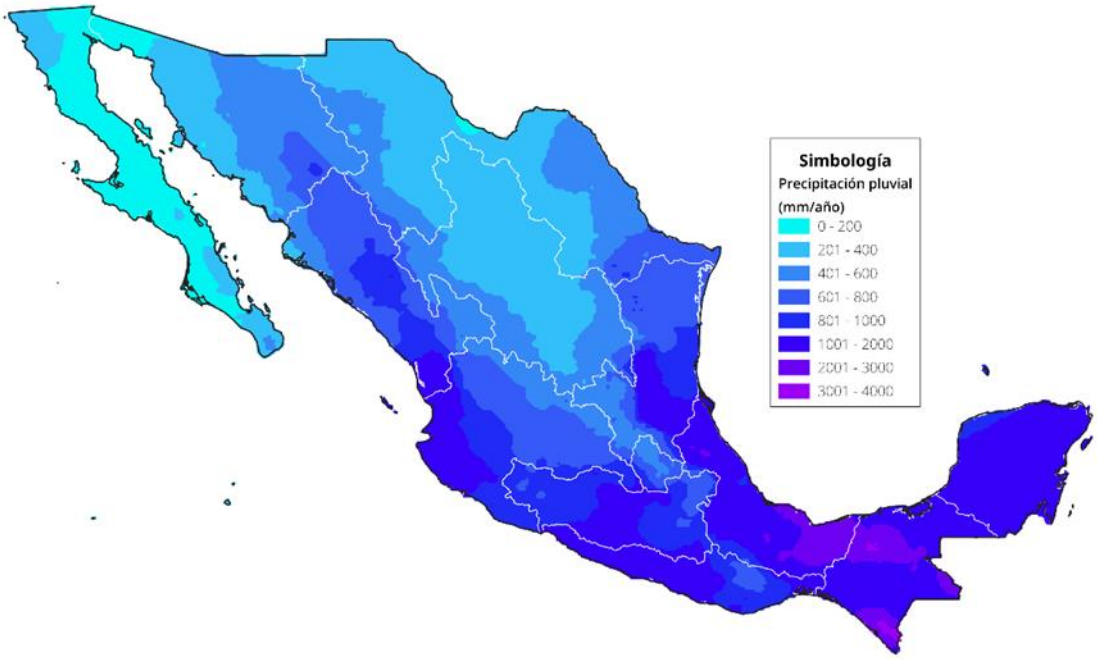

Fuente: CONAGUA. Estadísticas del Agua en México, 2023. Consultado en: https://sinav30.conagua.gob.mx:8080/Descargas/pdf/EAM2023_f.pdf [fecha de consulta: enero de 2026].

Precipitación

Su distribución a lo largo del año:

- Los meses de junio a octubre son los más lluviosos.
- Los meses de febrero a abril son los de menor precipitación.

Distribución de la precipitación pluvial promedio 1991-2020 y 2024 (mm) cambiar

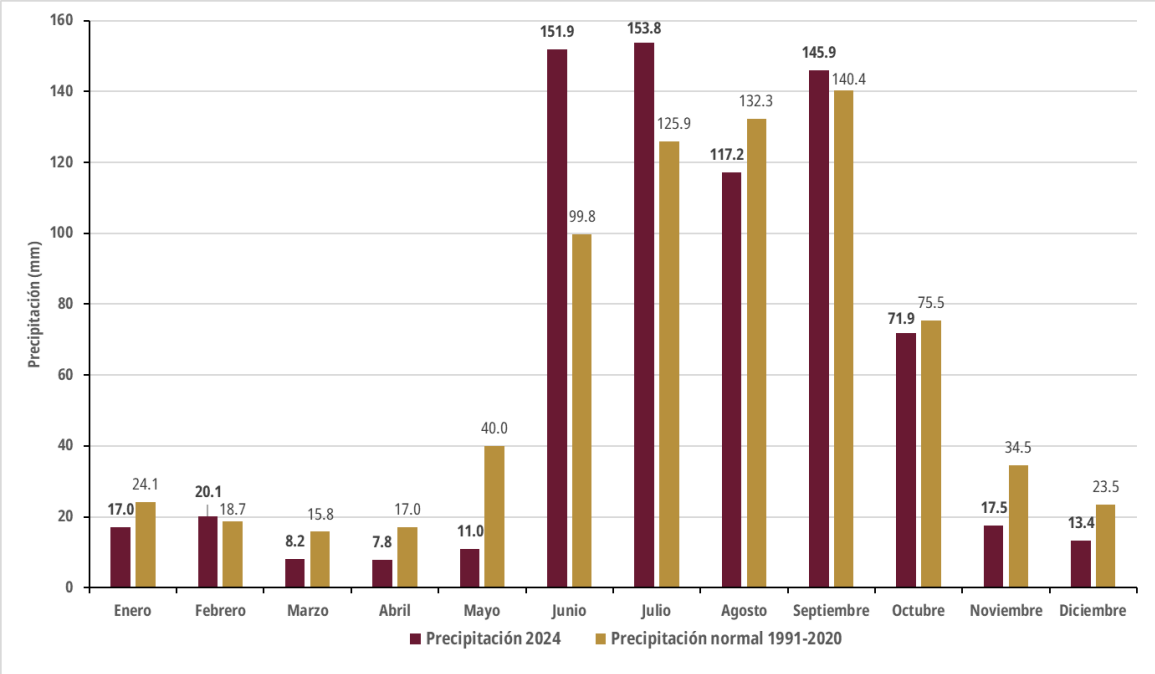

Fuente: CONAGUA. Coordinación General del Servicio Meteorológico Nacional.

Ciclones tropicales y huracanes

Por su ubicación geográfica intertropical, en el país se presentan periódicamente ciclones tropicales y huracanes[2].

Estos fenómenos ocasionan lluvias intensas que pueden causar inundaciones y daños, especialmente en zonas urbanas vulnerables.

También, contribuyen con el llenado de presas y lagos en tiempos relativamente cortos.

Los impactos se acentúan, entre otras razones, por:

- Carencia de sistemas adecuados de drenaje pluvial,
- Mala gestión de residuos sólidos (que obstruyen coladeras y desagües)
- Ubicación de asentamientos humanos en zonas de riesgo.
- El aumento de escurrimientos provenientes de zonas altas por la deforestación y erosión del suelo que reducen la capacidad de infiltración.

Los ciclones tropicales y huracanes serán más recurrentes y de mayor intensidad por los efectos del cambio climático.

Ciclones tropicales por categoría que han impactado el territorio nacional 1970 a 2024.

Océano	Depresiones tropicales	Tormentas tropicales	Huracanes moderados (H1 y H2)	Huracanes intensos (H3-H5)	Total
Atlántico	35	38	21	14	108
Pacífico	44	61	57	15	177
Total	**79**	**99**	**78**	**29**	**285**
Nota: Las cifras se derivan de la categoría de impacto y no de la categoría máxima alcanzada.					

Fuente: CONAGUA. Coordinación General del Servicio Meteorológico Nacional.

[2] Los huracanes son ciclones tropicales con velocidad de vientos mayor de 119 km/h.

Sequías

Cuando la escasez de lluvia permanece durante periodos largos, se presentan sequías[3]. En el país estas ocurren principalmente en la franja desértica del norte.

Las sequías de mayor intensidad y magnitud, suelen presentarse en ciclos aproximados de diez años, y su duración puede ser variable e impredecible.

Sus impactos son variados y afectan a las actividades productivas; dañan la vegetación y fauna silvestre e impactan la disponibilidad de las fuentes de abastecimiento de agua.

Monitor de Sequía de México 2025

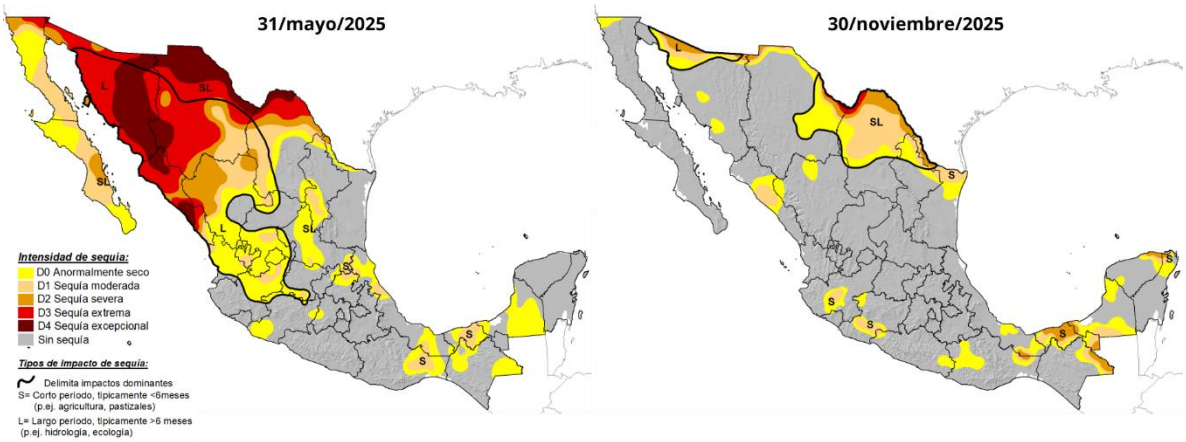

Fuente: CONAGUA. Monitor de Sequía en México. Consultado en: https://smn.conagua.gob.mx/es/climatologia/monitor-de-sequia/monitor-de-sequia-en-mexico [fecha de consulta: enero de 2026].

[3] Las sequías constituyen un fenómeno natural que se manifiesta como una deficiencia de humedad anormal y persistente, que tiene un impacto adverso en la vegetación, los animales y las personas. Consultado en: https://www.gob.mx/imta/articulos/que-son-las-sequias?idiom=es [fecha de consulta: enero de 2026].

a.2 Datos relevantes

Ríos y arroyos

Los ríos y arroyos de México constituyen una red hidrográfica de 633 mil kilómetros.

- En 51 ríos fluye el 85.7 % del escurrimiento superficial, cuyas cuencas abarcan el 65 % de la superficie territorial continental.
- En los siete ríos más caudalosos del país* fluye el 70 % del escurrimiento superficial.

Por la superficie que abarcan, destacan las cuencas de los ríos Bravo y Balsas; y por su longitud, los ríos Bravo y Grijalva-Usumacinta.

De las 757 cuencas hidrológicas del país, 104 están en condición de déficit.

Cuencas hidrológicas con disponibilidad y en déficit, 2023.

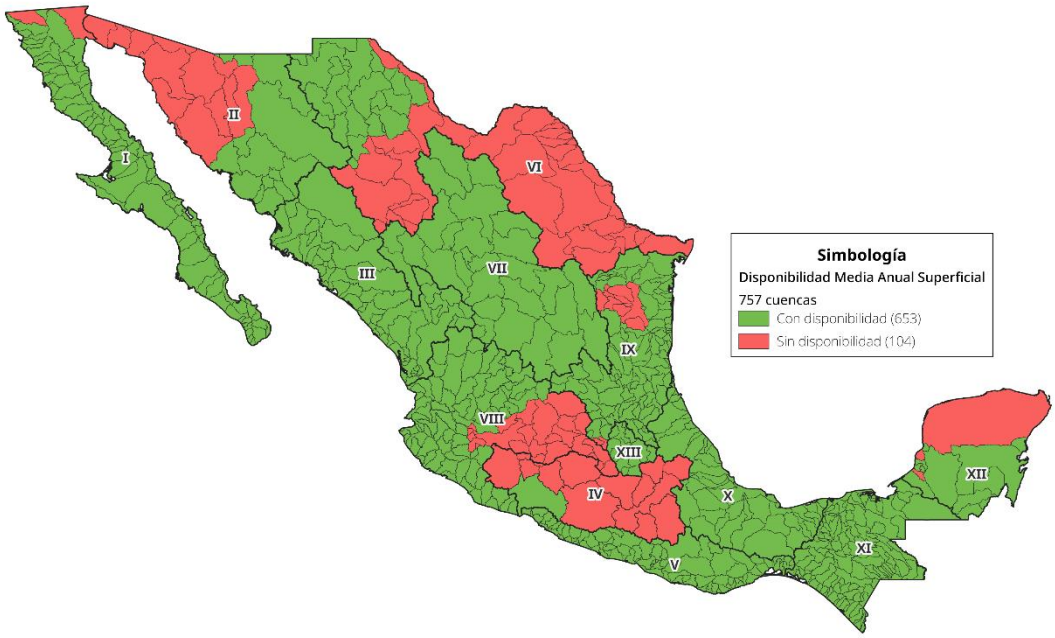

Fuente: CONAGUA. Elaboración propia con base en la publicación del DOF. Consultado en: https://www.dof.gob.mx/nota_detalle.php?codigo=5712948&fecha=28/12/2023#gsc.tab=0 [fecha de consulta: enero de 2026].

* Grijalva-Usumacinta, Papaloapan, Coatzacoalcos, Balsas, Pánuco, Santiago y Tonalá

Acuíferos

En el país, existen 653 acuíferos, de los cuales 114 se encuentran sobreexplotados.

El volumen de agua subterránea que se extrae en el país (36 165 hm^3, en 2023) representa solo al 35 % (casi la tercera parte) de la recarga (103 863 hm3).

Sobreexplotación de acuíferos

En las regiones áridas y semiáridas y las altamente pobladas como la del Valle de México, la extracción de agua subterránea es mayor a la recarga.

La sobreexplotación de los acuíferos provoca efectos adversos, entre otros:

- desabasto y agotamiento de manantiales
- deterioro de la calidad del agua
- incremento en los costos de extracción
- hundimientos y grietas del suelo
- afectaciones a la infraestructura y a los ecosistemas acuáticos

Acuíferos con disponibilidad y en déficit, 2023.

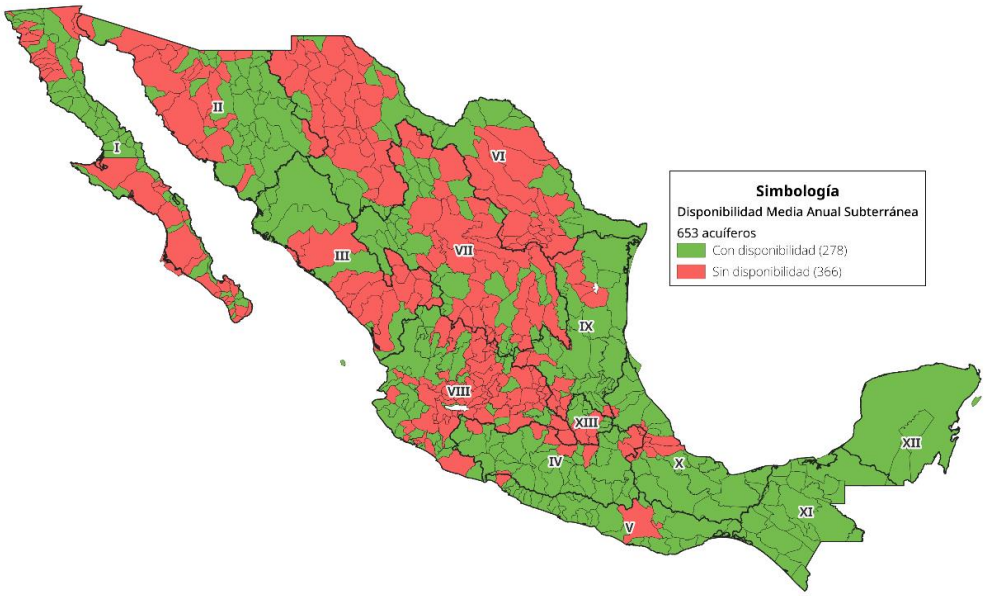

Fuente: Conagua. Elaboración propia con base en la publicación del DOF. Consultado en: https://www.dof.gob.mx/nota_detalle.php?codigo=5708074&fecha=09/11/2023#gsc.tab=0 [fecha de consulta: octubre de 2025]

Calidad del agua

La CONAGUA lleva a cabo el monitoreo sistemático de la calidad del agua de los principales cuerpos de agua del país a través de la Red Nacional de Medición de Calidad del Agua (RENAMECA).

La medición de la calidad del agua incluye el análisis de parámetros fisicoquímicos y microbiológicos, establecidos de acuerdo con el tipo de cuerpo de agua a caracterizar. El nivel de calidad de los cuerpos de agua se representa a través del semáforo de calidad del agua, el cual permite clasificar de manera cualitativa el estado del recurso hídrico, mediante un código de 3 colores (verde, amarillo y rojo).

Esta clasificación se obtiene a partir del análisis de los siguientes parámetros:

- Demanda Bioquímica de Oxígeno a cinco días
- Demanda Química de Oxígeno
- Sólidos Suspendidos Totales
- Coliformes Fecales
- Escherichia coli
- Enterococos Fecales
- Porcentaje de Saturación de Oxígeno Disuelto
- Toxicidad Aguda

El color verde del semáforo indica que la calidad del agua se encuentra en condiciones que van de excelentes a aceptable. En contraste, los colores amarillo y rojo indican que el agua se encuentra contaminada a fuertemente contaminada, representando el color rojo los contaminantes que más afectaciones podrían causar al ambiente.

De acuerdo con el semáforo de calidad del agua, de los 4 676 sitios superficiales monitoreados a través del RENAMECA durante el periodo 2012-2024:

- 44% se clasificaron en verde
- 26% en amarillo
- 30% en rojo

En el mapa 4 se muestran los sitios de monitoreo de aguas superficiales del país y los colores de semáforo de cada uno.

Mapa 4. Sitios superficiales de monitoreo de calidad del agua y su clasificación de acuerdo al semáforo de calidad del agua, 2012-2024

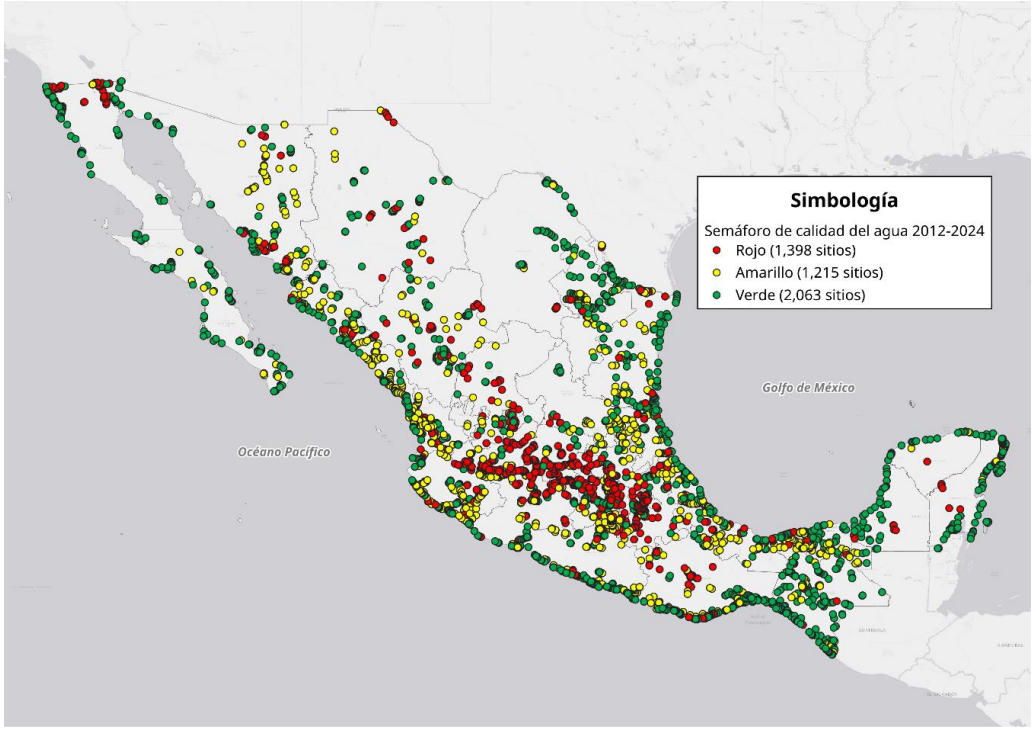

Fuente: CONAGUA. Calidad del Agua, 2012-2024. Consultado en: https://www.gob.mx/conagua/articulos/indicadores-de-calidad-del-agua [fecha de consulta: enero de 2026].

Población total, urbana y rural

En el periodo de 1950 a 2020, la población del país se concentra en las zonas urbanas, donde el número de habitantes se incrementó de 11 a 99 millones.

Los estados con mayor población rural son Chiapas (50.8 %) y Oaxaca (50.5 %), Hidalgo (42.7 %), Tabasco (41.5 %), Guerrero (40.3 %), Veracruz (38.3 %), Zacatecas (36.7 %) y San Luis Potosí (32.8%)[4].

Evolución de la población urbana, rural y total, 1950 a 2020

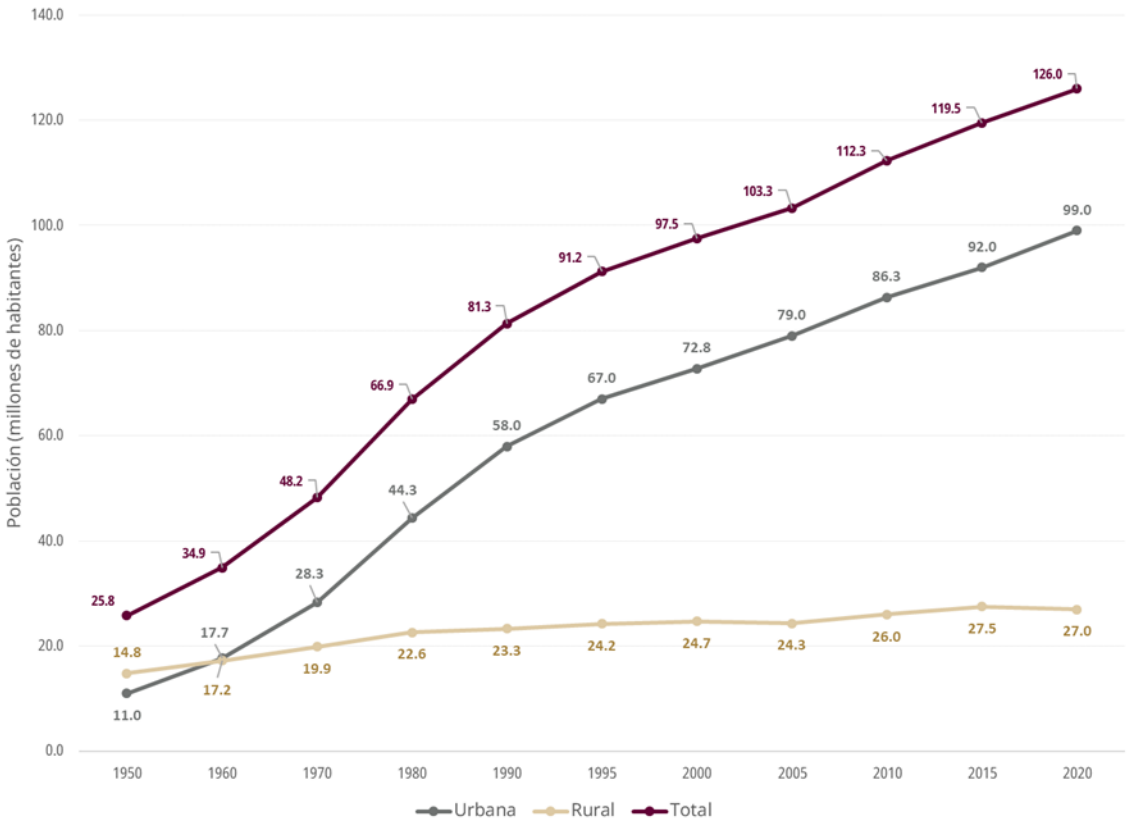

Fuente: CONAGUA. Estadísticas del Agua en México, 2023. Consultado en: https://sinav30.conagua.gob.mx:8080/Descargas/pdf/EAM2023_f.pdf [fecha de consulta: enero de 2026]

[4] INEGI. Cuéntame de México. Usa la estadística y la geografía para descubrir México. Consultado en: https://cuentame.inegi.org.mx/descubre/poblacion/rural_urbana/ [fecha de consulta: enero de 2026].

Agua renovable y desarrollo

La población (77 % del total) y la actividad económica (84 % del PIB) se concentran en las zonas norte y centro del país, donde se tiene la menor disponibilidad de agua (31.7 % del agua renovable[5]).

En contraste, en la zona sur sureste, en donde se ubica el 23 % de la población y se produce el 16 % del PIB, se dispone del 68 % del agua renovable.

Contraste regional entre agua renovable y desarrollo 2024

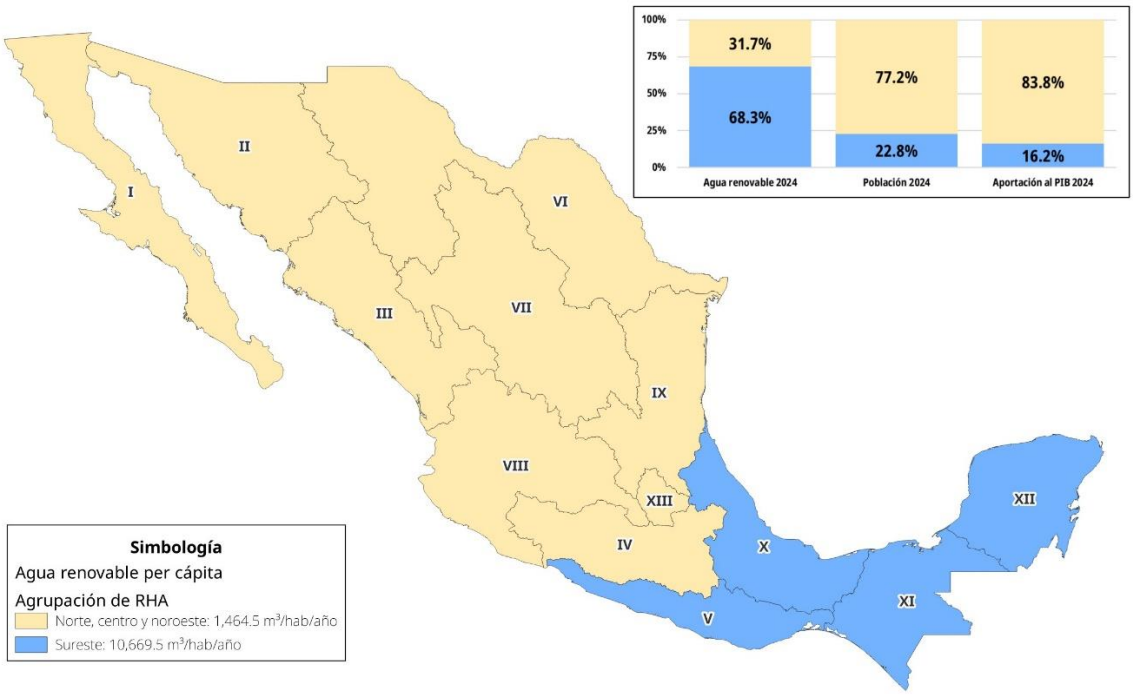

Fuente: Conagua. Gerencia de Planificación Hídrica.

[5] Agua renovable se refiere a la cantidad máxima de agua que puede ser extraída o utilizada anualmente en un área sin alterar el equilibrio ecológico, y que se repone a través del ciclo hidrológico, principalmente por la lluvia.

Usos del agua

En 2023, el volumen de agua concesionado en el país fue de 267 350 hm^3: 176 721 hm^3 son de usos no consuntivos y 90 629 hm3 de usos consuntivos.

En cuanto a los usos no consuntivos, se concesionaron 176 711 hm3 para la generación de energía hidroeléctrica y 9.5 hm3 para la conservación ecológica

Del volumen concesionado para uso consuntivo, 76 % se distribuye para uso agrícola, 14.9 % para abastecimiento público, 4.6 % para la industria autoabastecida y 4.5 % para la generación de energía (excepto hidroelectricidad).

Volúmenes anuales de agua concesionados para uso consuntivo (diciembre de 2023).

Uso	Origen				Volumen total (miles de hm^3)	%
	Superficial (miles de hm^3)	%	Subterráneo (miles de hm^3)	%		
Abastecimiento público[1]	5.93	10.9	7.57	20.9	13.5	14.9
Agrícola[2]	43.19	79.3	25.71	71.1	68.89	76.0
Industria autoabastecida[3]	1.69	3.1	2.51	7.0	4.2	4.6
Termoeléctricas	3.65	6.7	0.38	1.0	4.04	4.5
Total	54.46	100.0	36.17	100.0	90.63	100.0

Fuente: CONAGUA. Subdirección General de Administración del Agua.

1 Incluye doméstico y público urbano.

2 Incluye agrícola, acuacultura, pecuario, múltiple y otros.

3 Incluye agroindustrial, servicios, industrial y comercio.

Agua potable y alcantarillado

En 2020, de acuerdo con el Censo de Población y Vivienda, la cobertura de agua potable a nivel nacional es de 96.1 % y la de alcantarillado, de 95.2 %. En zonas urbanas, la cobertura de agua potable fue de 98 % y en zonas rurales, 89.1 %; en cuanto a alcantarillado, la cobertura respectiva fue de 98.5 % y 83.2 % [6].

Se destaca que en 21 entidades federativas se presentan coberturas de agua potable entubada en vivienda o predio por arriba del valor nacional. La población servida a nivel nacional es de 120.5 millones de habitantes en el año 2020.

En cuanto al alcantarillado, 19 entidades federativas registran coberturas superiores al valor nacional de 95.2%. La población atendida con este servicio en el país superaba los 119.3 millones de habitantes en 2020.

Coberturas de agua potable y alcantarillado, 2020

Entidad Federativa	Agua potable		Alcantarillado	
	Población servida (hab.)	Población servida (%)	Población servida (hab.)	Población servida (%)
Aguascalientes	1 410 516	99.3	1 409 513	99.3
Baja California	3 641 772	97.7	3 583 608	96.1
Baja California Sur	744 338	94.1	766 262	96.9
Campeche	884 512	95.6	873 972	94.4
Coahuila de Zaragoza	3 099 677	98.9	3 093 057	98.6
Colima	720 473	99.1	722 497	99.3
Chiapas	4 901 069	88.9	4 944 459	89.7
Chihuahua	3 651 910	98.1	3 576 287	96.1
Ciudad de México	9 023 868	98.7	9 123 074	99.7
Durango	1 774 075	97.5	1 711 896	94.1
Guanajuato	5 947 867	96.9	5 933 458	96.6
Guerrero	3 100 018	88.1	3 052 311	86.7
Hidalgo	2 949 280	96.0	2 920 828	95.1
Jalisco	8 181 452	98.6	8 176 061	98.6
México	16 435 872	97.1	16 439 948	97.2
Michoacán de Ocampo	4 584 390	97.1	4 506 697	95.4
Morelos	1 873 566	95.7	1 922 246	98.2
Nayarit	1,184 616	96.9	1 162 236	95.0

[6] CONAGUA. Situación del Subsector Agua Potable, Alcantarillado y Saneamiento edición 2025. Consultado en www.gob.mx/cms/uploads/attachment/file/1044537/DSAPAS_2025.pdf [fecha de consulta: enero de 2026].

Entidad Federativa	Agua potable		Alcantarillado	
	Población servida (hab.)	Población servida (%)	Población servida (hab.)	Población servida (%)
Nuevo León	5 706 110	98.9	5 694 653	98.7
Oaxaca	3 682 391	89.8	3 262 760	79.6
Puebla	6 246 575	95.2	6 225 163	94.9
Querétaro	2 302 578	97.6	2 291 312	97.1
Quintana Roo	1 797 700	97.2	1 789 789	96.8
San Luis Potosí	2 594 712	92.3	2 543 827	90.5
Sinaloa	2 938 997	98.5	2 893 519	97.0
Sonora	2 878 972	98.6	2 767 398	94.8
Tabasco	2 246 119	93.8	2 341 723	97.8
Tamaulipas	3 450 766	98.2	3 331 602	94.8
Tlaxcala	1 306 033	97.6	1 294 906	96.7
Veracruz de Ignacio de la Llave	7 331 237	91.3	7 265 754	90.5
Yucatán	2 285 195	98.8	2 133 601	92.2
Zacatecas	1 584 868	98.1	1 557 230	96.3
Total Nacional	120 461 524	96.1	119 311 647	95.2

FUENTE: INEGI. Censo de Población y Vivienda (CPV) 2020. Consultado en: https://www.inegi.org.mx/programas/ccpv/2020/#tabulados [fecha de consulta: enero de 2026].

Tratamiento de aguas residuales municipales

En 2023, en nuestro país, las 2 928 plantas municipales en operación trataron un caudal de 143.57 m3/s de los 214.3 m3/s recolectados por los sistemas de alcantarillado, lo que representa una cobertura del 67 %.

Plantas municipales de aguas residuales tratadas, por entidad federativa, 2024

Entidad Federativa	Núm. de plantas	Capacidad instalada (l/s)	Caudal tratado (l/s)	Cobertura de tratamiento (%)
Aguascalientes	135	4 849	2 696	97.0
Baja California	42	6 617	5 044	99.7
Baja California Sur	31	2 060	1 416	66.0
Campeche	28	159	123	5.9
Coahuila de Zaragoza	26	5 732	4 677	68.9
Colima	69	2 299	1 727	72.1
Chiapas	135	2 310	1 348	25.6
Chihuahua	208	9 485	7 097	87.2
Ciudad de México	30	5 583	21 589	99.2
Durango	244	5 861	4 098	97.4
Guanajuato	93	8 412	5 034	79.3
Guerrero	46	3 012	2 846	73.3
Hidalgo[1]	108	35 899	493	22.7
Jalisco	155	16 241	12 033	91.9
México[2]	129	9 005	18 291	70.3
Michoacán de Ocampo	43	4 119	2 702	44.2
Morelos	78	3 162	2 239	33.5
Nayarit	75	3 890	2 217	99.8
Nuevo León	57	16 167	11 519	90.8
Oaxaca	70	1 864	1 187	47.1
Puebla	152	4 315	4 158	55.7
Querétaro de Arteaga	64	2 375	1 808	69.9
Quintana Roo	29	3 042	2 025	53.5
San Luis Potosí	49	2 636	1 847	50.9
Sinaloa	318	6 736	5 347	67.0
Sonora	112	7 414	6 074	62.9
Tabasco	103	3 153	2 358	33.0
Tamaulipas	65	8 023	4 551	89.0

Entidad Federativa	Núm. de plantas	Capacidad instalada (l/s)	Caudal tratado (l/s)	Cobertura de tratamiento (%)
Tlaxcala	24	1 097	1 080	69.8
Veracruz de Ignacio de la Llave	92	6 910	4 281	30.9
Yucatán	37	759	575	14.5
Zacatecas	52	1 726	1 290	54.0
Total Nacional	**2 899**	**194 914**	**143 770**	**68.1**

1/ La capacidad instalada incluye los 35 000 l/s la planta Atotonilco.
2/ El caudal tratado incluye el que se procesa en la PTAR Atotonilco, ubicada en el estado de Hidalgo, 19 029.6 l/s de la CDMX y 12 686.4 l/s del Estado de México.

Fuente: CONAGUA. Situación del Subsector Agua Potable, Alcantarillado y Saneamiento. Edición 2025. Consultado en: www.gob.mx/cms/uploads/attachment/file/1044537/DSAPAS_2025.pdf [fecha de consulta: enero de 2026].

Agua potable y mortalidad por enfermedades diarreicas en niños

La falta de agua limita las prácticas básicas de higiene y facilita la propagación de enfermedades prevenibles, como infecciones gastrointestinales y respiratorias, al impedir la eliminación eficaz de virus y bacterias.

En México, la tasa de mortalidad infantil, en menores de cinco años, por cada 100 000 habitantes, se redujo notablemente al pasar de 122.7 en 1990 a 42.1 en 1995 y continuó disminuyendo hasta 5.4 en el año 2024.

Cobertura de agua potable y alcantarillado y tasa de mortalidad por enfermedades diarreicas en menores de cinco años, 1990 a 2024

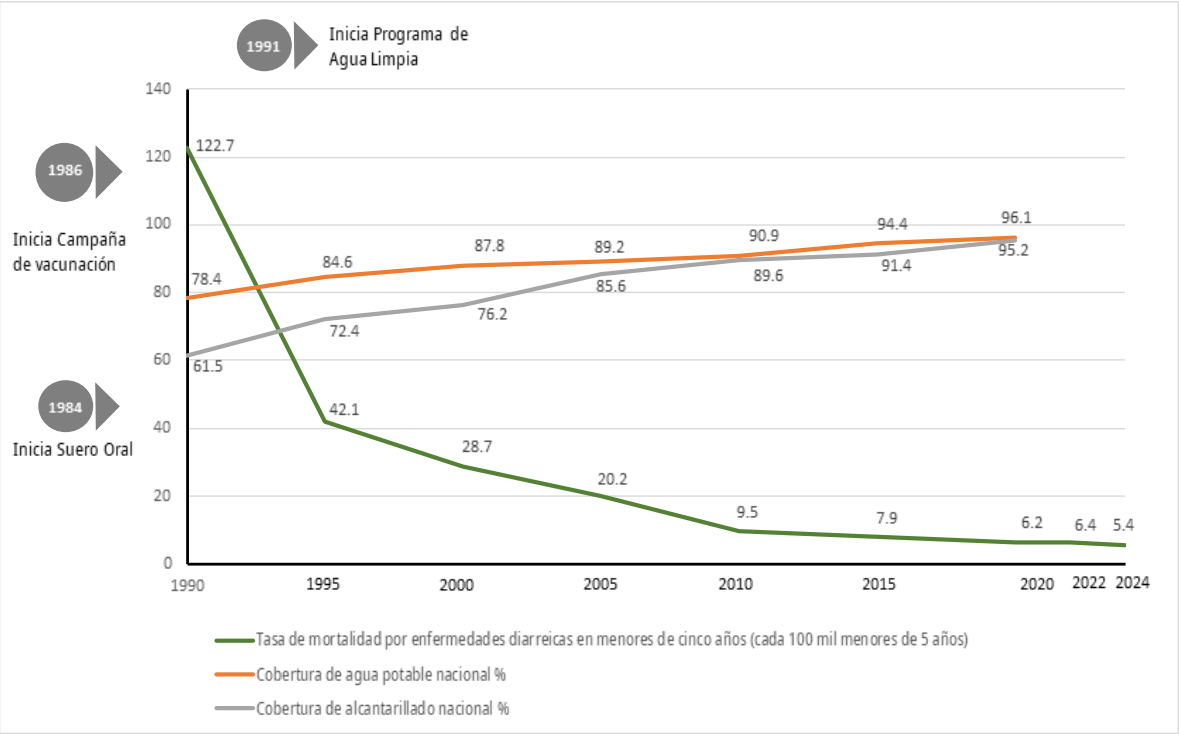

Fuente: INEGI (2020), SALUD (2025)

Brechas de acceso a agua entubada y saneamiento básico por Entidad Federativa

Según la ENIGH 2024, en Guerrero solo el 16.5 % de la población cuenta con acceso diario a agua entubada y saneamiento básico[7], mientras que en Nuevo León el 91.6 % cuenta con estos servicios, por lo que existe una brecha en el acceso a los mismos, según el nivel de desarrollo de ambas entidades federativas.

El promedio nacional de la población que tienen acceso a dichos servicios es 56.3 %, las 14 entidades que se encuentran por debajo de este son las más rezagadas al respecto: Nayarit, Michoacán, Veracruz, Tlaxcala, San Luis Potosí, Hidalgo, México, Zacatecas, Chiapas, Oaxaca, Morelos, Puebla, Baja California Sur y Guerrero.

Proporción de la población que tiene acceso diario a agua entubada y saneamiento básico, 2024

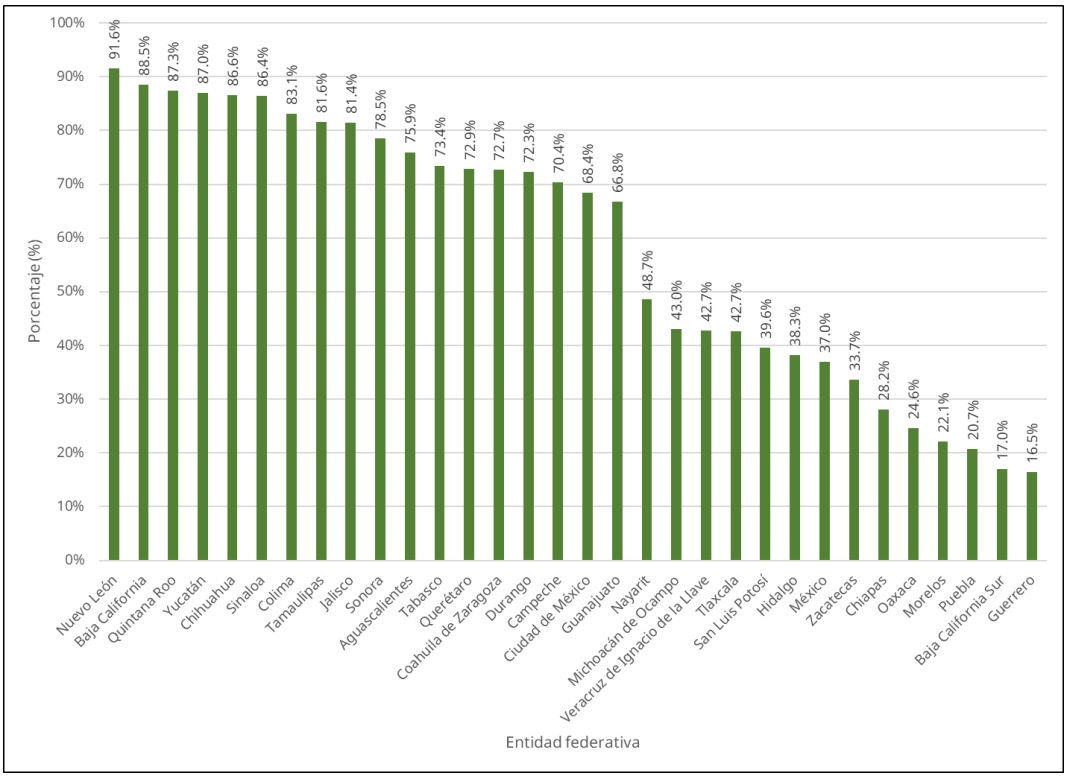

Fuente: INEGI. Encuesta Nacional de Ingresos y Gastos de los Hogares (ENIGH) 2024, Consultado en: https://www.inegi.org.mx/programas/enigh/nc/2024/ [fecha de consulta: enero de 2026]

[7] Agua entubada dentro de la vivienda o fuera de ella, pero dentro del predio, con una dotación diaria de agua, sanitario de uso exclusivo y drenaje conectado a la red o fosa séptica.

Brechas de acceso a agua entubada y a saneamiento básico por Entidad Federativa, según nivel socioeconómico

En México, existe una brecha en la frecuencia del acceso a agua entubada, así como a al saneamiento básico, según el nivel socioeconómico de los hogares; esta desigualdad varía considerablemente en todo el territorio nacional.

Por ejemplo, La Ciudad de México muestra una brecha amplia en la frecuencia del acceso a agua entubada y al saneamiento entre los hogares de las Alcaldías Miguel Hidalgo y Xochimilco y Milpa Alta; la primera, se caracteriza por el alto nivel socioeconómico de los hogares asentados ahí y por el acceso diario a esos servicios, en tanto que las últimas dos tienen hogares de bajo nivel socioeconómico y una menor frecuencia en el acceso a los servicios.

Proporción de la población que tiene acceso diario al agua entubada, así como el saneamiento básico en la Ciudad de México

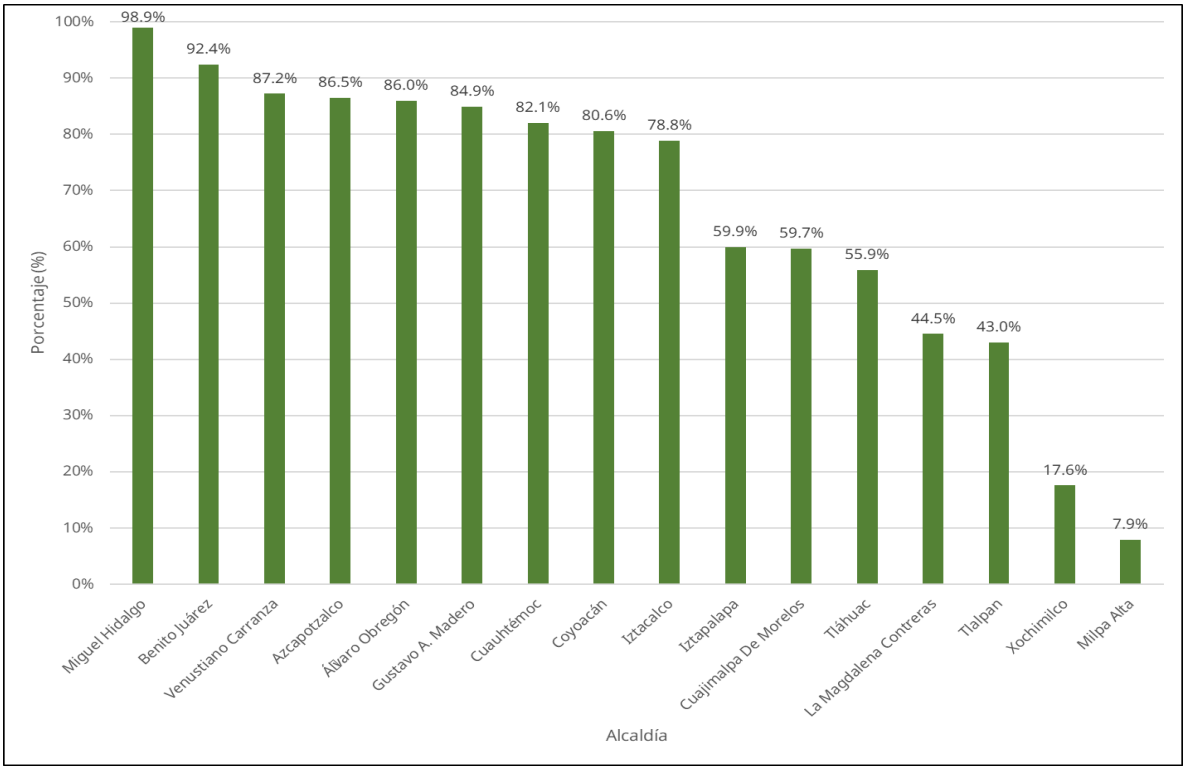

Fuente: INEGI, Encuesta Nacional de Ingresos y Gastos de los Hogares (ENIGH) 2024. Consultado en: https://www.inegi.org.mx/programas/enigh/nc/2024/ [consulta: enero de 2026]

Grado de presión por Región Hidrológico-Administrativa

En el país se utiliza el 19.2 % del volumen de agua renovable, por lo que el grado de presión es considerado bajo.

En el centro, norte y noroeste, el grado de presión es alto, mientras que en el sur y sureste es bajo.

En el centro, norte y noroeste del país existen zonas que utilizan más del 40 % del agua renovable, lo que limita el desarrollo socioeconómico.

La RHA XIII Aguas del Valle de México, registra un elevado grado de presión (128.7 %), esto es, se utiliza más agua de la que naturalmente se dispone en la cuenca.

Grado de presión sobre el recurso hídrico por Región Hidrológico-Administrativa, 2023

Región Hidrológico Administrativa		Agua renovable (hm^3/año)	Volumen total de agua concesionado (hm^3/año)	Grado de Presión (%)	Grado
I	Península de Baja California	5 026	4 457	88.7	Alto
II	Noroeste	8 269	6 883	83.2	Alto
III	Pacífico Norte	27 100	10 787	39.8	Medio
IV	Balsas	24 216	11 365	46.9	Alto
V	Pacífico Sur	31 730	1 709	5.4	Sin estrés
VI	Río Bravo	13 518	9 985	73.9	Alto
VII	Cuencas Centrales del Norte	4 744	4 027	84.9	Alto
VIII	Lerma-Santiago-Pacífico	35 593	16 184	45.5	Alto
IX	Golfo Norte	28 169	6 032	21.4	Medio
X	Golfo Centro	117 522	6 451	5.5	Sin estrés
XI	Frontera Sur	153 544	2 762	1.8	Sin estrés
XII	Península de Yucatán	19 320	5 555	28.8	Medio
XIII	Aguas del Valle de México	3 445	4 434	128.7	Muy Alto
Total Nacional		472 195	90 629	19.2	Bajo

Nota: Grado de presión sobre el recurso hídrico = 100*(Volumen total de agua concesionado / Agua renovable).

Fuente: CONAGUA, Subdirecciones Generales Técnica y de Administración del Agua.

Agua renovable per cápita a nivel regional

El agua renovable per cápita a nivel regional tiene grandes contrastes.

En la RHA XIII Aguas del Valle de México, se tienen 141 m^3/hab/año, mientras que en la RHA XI Frontera Sur es 5 veces el valor nacional y 126 veces el de la RHA XIII.

Agua renovable per cápita por Región Hidrológico Administrativa, 2024.

Región Hidrológico-Administrativa		Agua renovable (hm^3/año)	Población regional (Millones de habitantes)	Agua renovable per cápita (m^3/hab/año)
I	Península de Baja California	4 731	5.17	915
II	Noroeste	8 495	2.99	2 843
III	Pacífico Norte	27 169	4.75	5 716
IV	Balsas	24 079	12.88	1 869
V	Pacífico Sur	31 832	5.35	5 948
VI	Río Bravo	12 350	14.36	860
VII	Cuencas Centrales del Norte	5 201	5.01	1 037
VIII	Lerma-Santiago-Pacífico	35 613	27.16	1 311
IX	Golfo Norte	28 407	5.33	5 329
X	Golfo Centro	120 164	10.83	11 093
XI	Frontera Sur	150 907	8.52	17 718
XII	Península de Yucatán	19 320	5.50	3 513
XIII	Aguas del Valle de México	3 444.8	24.42	141
	Total Nacional	471 712	132.27	3 566

Nota: el agua renovable media per cápita se calcula con base en el Censo de Población y Vivienda 2020 de INEGI y proyecciones de población de CONAPO.

Fuente: CONAGUA. Subdirección General Técnica (2024), CONAPO (2024).

Gobierno de
México